Disputa partidária e comportamento político nos bairros ricos de São Paulo (2012–2024)

Rascunho integrado de evidência empírica
para o projeto de dissertação de mestrado

Candidato: Thiago Suzuki Conti Miaguchi
Programa: Pós-Graduação em Ciência Política — DCP/FFLCH/USP
Orientadores indicados: Bruno Wilhelm Speck, Glauco Peres da Silva
Referência teórica adicional: Eduardo Marques (FLS 6195)

Este documento integra três frentes empíricas desenvolvidas como rascunho de capítulos empíricos da dissertação: (I) sistema partidário e recomposição eleitoral, (II) financiamento eleitoral e reorganização material da política, (III) sociologia urbana institucional e mapeamento ideológico. Todas as evidências usam dados públicos do TSE, IBGE e CEM/USP, com código aberto em github.com/miaguchi/democracia-em-dados.

Sumário executivo

Este documento apresenta três descobertas empíricas sobre o comportamento eleitoral nos bairros ricos de São Paulo entre 2012 e 2024, organizadas em três eixos que correspondem às agendas de pesquisa dos orientadores indicados no projeto original.

Descoberta 1 — Divergência interna aos bairros ricos. Pinheiros (Z251) e Indianópolis (Z258), empates em renda per capita (R$ 3.819 e R$ 3.504) e ambas dominadas pelo PSDB em 2012 (~48% do voto), divergiram radicalmente até 2024: Pinheiros tem PSOL como partido #1 (28%), enquanto Indianópolis tem PL liderando (20%) com bloco direita lato sensu somando 82%. **Mesma origem, destinos opostos em 12 anos.**

Descoberta 2 — Reorganização material do financiamento. Três eras regulatórias deixaram assinaturas distintas: em 2012, recursos PJ dominavam os bairros ricos (construtoras doando ~24% do total para vereadores); em 2016, após a reforma, pessoa física subiu a 41% do total; em 2020-2024, o FEFC reocupou o espaço com 87% do financiamento via partido. **A democratização do financiamento durou apenas uma eleição (2016)**; o Fundo Especial substituiu o modelo empresarial sem passar pelo doador individual.

Descoberta 3 — O ambiente institucional cultural-progressista foi politicamente ativado entre 2016 e 2024. A renda per capita das zonas eleitorais explica apenas 9% da variância ideológica. Um índice de densidade institucional construído com a base CEM/USP (universidades, escolas particulares progressistas, escolas públicas de prestígio, instituições culturais internacionais) explica **44% da variância do escore ideológico de vereador em 2024** (R^2 cinco vezes maior que renda). E o dado mais surpreendente: em 2016, essa mesma correlação era **próxima de zero** — o ambiente institucional só começou a "falar" politicamente depois do ciclo impeachment-Bolsonaro-Lula que ativou ideologicamente o eleitorado (compatível com Inglehart & Norris, 2016/2019).

Convergência temporal. Os três eixos mostram ativação simultânea: o realinhamento partidário, a transformação do financiamento e a emergência do índice institucional como preditor acontecem **entre 2016 e 2020**, consolidando-se em 2024. Não são fenômenos independentes — são manifestações paralelas de um mesmo rearranjo estrutural do campo político-territorial paulistano.

Parte 0 — Introdução

Pergunta de pesquisa e recorte empírico

A pergunta central do projeto de dissertação (Miaguchi, 2023) é: *"a nível infra-municipal, de 2012 a 2022, em bairros ricos da cidade de São Paulo, as preferências eleitorais demarcam continuidades, oscilações ou rupturas ideológicas no voto?"* Este documento estende o período original até 2024 (última eleição municipal disponível) e testa empiricamente as quatro hipóteses formuladas na proposta:

H1 — há um novo padrão de preferências eleitorais nas zonas ricas que não se relaciona a movimento pendular ou a força centrípeta em torno da centro-direita.

H2 — a maior pluralização dos grupos de interesse implica novo padrão de competição política, volatilidade eleitoral e representação no legislativo.

H3 — o recrutamento e as disputas intrapartidárias da centro-direita ao longo do tempo produziram absorção pela direita e extrema-direita.

H4 — o voto da esquerda nos bairros mais ricos e homogêneos aponta para outras variáveis independentes do que a renda ou a escolaridade.

Recorte empírico. O projeto original indica as zonas 5ª (Jardim Paulista), 251ª (Pinheiros) e 258ª (Indianópolis) como unidades-chave. Este documento expande o recorte para o "corredor das universidades" — Bela Vista (1ª), Perdizes (2ª), Santa Ifigênia (3ª), Jardim Paulista (5ª), Vila Mariana (6ª), Pinheiros (251ª), Indianópolis (258ª) e Butantã (346ª) — e usa as 58 zonas eleitorais de SP como universo de comparação.

Dados primários. TSE (votacao_partido_munzona, votacao_candidato_munzona, votacao_secao, prestacao_contas, consulta_cand) para 2012, 2016, 2020, 2024; base de locais de votação georreferenciados EL2022_LV_ESP_CEM_V2 do Centro de Estudos da Metrópole (CEM/USP); Censo 2010 por setor censitário (IBGE); geometrias IBGE via pacote *geobr*. Escores ideológicos partidários de Bolognesi, Ribeiro & Codato (2023).

Metodologia geral

Três ferramentas analíticas são usadas em todas as partes:

(a) Volatilidade de Pedersen (1979), decomposta conforme Bartolini & Mair (1990) em componentes *entre-blocos* (realinhamento real) e *dentro-blocos* (rotação intra-campo ideológico). Permite distinguir mudança de rótulo partidário de mudança de posição política.

(b) Escore ideológico médio ponderado por votos, usando os escores de Bolognesi et al. (2023) (expert survey ABCP, escala 0–10 onde 0 é extrema-esquerda e 10 é extrema-direita). Para cada zona eleitoral, média dos escores dos partidos com peso pelos votos recebidos.

(c) Plurality bipartite por seção eleitoral — classifica cada seção pelo bloco (esquerda+centro-esquerda vs centro-direita+direita) que somou mais votos. Métrica discreta, útil para identificação territorial de padrões quase-maiorias.

Todas as três métricas são reportadas quando relevantes, e complementam-se: a (a) isola a dimensão de sistema partidário, a (b) permite regressões contínuas, a (c) responde a pergunta

"onde a esquerda venceu?" em forma concreta.

Parte I — Sistema partidário (2012–2024)

Evidência para H1 e H3. Agenda: sistemas partidários subnacionais, volatilidade, reorganização eleitoral. Ferramental metodológico afinado com a agenda do prof. Glauco Peres da Silva.

1.1 A mesma origem, destinos opostos: Pinheiros × Indianópolis

A tabela abaixo mostra o top 6 de partidos por voto de vereador em duas zonas-chave — Pinheiros (Z251) e Indianópolis (Z258), 2ª e 3ª mais ricas de SP por renda per capita — em quatro ciclos municipais consecutivos:

Ano	Pinheiros — top partidos	Indianópolis — top partidos
2012	PSDB 48% · PT 17% · PV 12% · PPS 9% · PSD 9% · PMDB 6%	PSDB 47% · PV 13% · PSD 13% · PT 12% · PPS 8% · PMDB 8%
2016	**PSDB 36%** · NOVO 20% · PT 19% · PSOL 12% · PV 8% · Rede 6%	**PSDB 45%** · NOVO 19% · PT 13% · PV 10% · DEM 7% · PSOL 7%
2020	**PSOL 28%** · NOVO 24% · PSDB 18% · PT 14% · Rede 8% · PSD 8%	**NOVO 29%** · PSDB 24% · PSOL 17% · PSD 12% · PT 10% · Patriota 9%
2024	**PSOL 28%** · NOVO 18% · PT 17% · PSB 13% · PL 12% · Rede 11%	**PL 20%** · PSOL 18% · NOVO 18% · UNIÃO 17% · PP 14% · MDB 13%

Em 2012, as duas zonas são quase indistinguíveis: PSDB domina com ~48% do voto e a distribuição dos partidos restantes é similar. Em 2024, elas estão em polos opostos:

Pinheiros: PSOL vira o partido #1 em 2020 e mantém a posição em 2024. O bloco esquerda+centro-esquerda (PSOL+PT+PSB+PDT+Rede) soma 69% do voto principal em 2024.

Indianópolis: PSDB colapsa entre 2016 e 2024 (de 45% para virtualmente zero) e o voto de direita se fragmenta em cinco partidos — PL, NOVO, UNIÃO, PP, MDB — que somam 82% do voto principal. A esquerda se reduz a um PSOL residual (18%).

A H1 fica empiricamente confirmada: não houve movimento pendular nem força centrípeta. Houve **divergência estrutural** entre zonas que começaram no mesmo ponto. A causa não pode ser renda (empatadas) nem escolaridade (ambas altas) — hipóteses testadas diretamente na Parte III deste documento.

1.2 Volatilidade Pedersen e decomposição por bloco

A métrica clássica de volatilidade eleitoral é o **Índice de Pedersen** (Pedersen, 1979), definido entre dois pleitos consecutivos como:

$V = (1/2) \cdot \Sigma_i |p_{i,t+1} - p_{i,t}|$, onde $p_{i,t}$ é a proporção de votos do partido i no tempo t.

Pedersen vai de 0 (nenhuma mudança) a 1 (substituição total dos partidos). Aplicado ao voto de vereador em SP entre 2020 e 2024, a média da volatilidade bruta das 57 zonas é **0,257** — na faixa "alta" da literatura europeia clássica de sistemas partidários. No prefeito 1º turno, a média é ainda maior: **0,673**.

Mas Pedersen bruto **não distingue** mudança substantiva de mudança cosmética. Se um eleitor troca PT por PSOL, isso conta como volatilidade da mesma forma que se troca PT por PL — apesar das implicações ideológicas serem radicalmente distintas. **Bartolini & Mair (1990)** propõem decompor Pedersen em dois componentes:

V_total = V_entre_blocos + V_dentro_blocos

Onde *V_entre_blocos* é a volatilidade calculada sobre os agregados dos partidos em blocos ideológicos (esquerda, centro, direita), e *V_dentro_blocos* é o restante — rotação interna a cada bloco. A interpretação teórica é direta: **V_entre mede realinhamento ideológico genuíno; V_dentro mede reordenamento interno sem mudança de lado**.

1.2.1 Classificação dos partidos: escala Bolognesi et al. (2023)

Para decompor, precisamos classificar os partidos em blocos. Usamos os escores do **expert survey da ABCP** conduzido por Bolognesi, Ribeiro & Codato (2023), que posicionam cada partido em uma escala contínua 0–10 (0 = extrema-esquerda, 10 = extrema-direita). A tabela a seguir mostra os escores dos principais partidos presentes no voto de SP 2020–2024, aplicados retroativamente aos partidos hoje reagrupados em federações:

Partido	Escore	Bloco tripartite	Bloco quintipartite
PSOL	1,28	esquerda	esquerda
PCdoB	1,92	esquerda	esquerda
PT	2,97	esquerda	esquerda
Fed. PSOL/Rede (média)	3,03	esquerda	centro-esquerda
Fed. PT/PCdoB/PV (média)	3,39	esquerda	centro-esquerda
PDT	3,92	esquerda	centro-esquerda
PSB	4,05	esquerda	centro-esquerda
Rede (isolado)	4,77	centro	centro
Cidadania	4,92	centro	centro
PV	5,29	centro	centro
Fed. PSDB/Cidadania (média)	6,02	direita	centro-direita
PTB	6,10	direita	centro-direita
Avante	6,32	direita	centro-direita
MDB	**7,01**	**direita**	**direita***
PSD	7,09	direita	direita
PSDB (isolado)	7,11	direita	direita
PL (ex-PR)	7,78	direita	direita
Republicanos	7,78	direita	direita
PSL	8,11	direita	direita
NOVO	8,13	direita	direita

PP (Progressistas)	8,20	direita	direita
União Brasil (DEM+PSL)	8,34	direita	extrema-direita
Patriota	8,55	direita	extrema-direita
DEM	8,57	direita	extrema-direita

**MDB cai em 7,01, a 0,01 pontos do limiar entre centro-direita (5,51–7,00) e direita (7,01–8,50). Esta sensibilidade é discutida em 1.2.3.*

Os limiares usados pelo próprio paper de Bolognesi et al. dividem a escala em 7 blocos: extrema-esquerda (0–1,50), esquerda (1,51–3,00), centro-esquerda (3,01–4,49), centro (4,50–5,50), centro-direita (5,51–7,00), direita (7,01–8,50) e extrema-direita (8,51–10). Para a decomposição de Pedersen, testamos duas agregações: **tripartite** (esquerda / centro / direita) e **quintipartite** (esquerda / centro-esquerda / centro / centro-direita / direita).

1.2.2 Decomposição em duas escalas

A decomposição produz resultados **dramaticamente diferentes** conforme a granularidade do agrupamento:

Cargo	V_total	Tripartite V_entre	Tripartite %	Quintipartite V_entre	Quintipartite %
Vereador	0,257	0,007	**2,6%**	0,144	**55,8%**
Prefeito 1T	0,673	0,042	**6,2%**	0,352	**52,3%**

A leitura tripartite sugere que quase toda a volatilidade é intra-campo — só 2,6% no vereador e 6,2% no prefeito vêm de cruzamento entre esquerda, centro e direita. A interpretação seria: "o eleitorado paulistano não mudou de lado ideológico; apenas trocou de legenda dentro do mesmo campo". Essa é uma leitura *conservadora* — que contraria narrativas de "virada à direita" que a imprensa costuma usar — mas ela depende criticamente do limiar usado.

A leitura quintipartite muda completamente o quadro. Quando separamos centro-esquerda de centro e centro-direita de direita, mais da metade da volatilidade aparece como *entre* blocos: **55,8% no vereador e 52,3% no prefeito**. A diferença entre as duas leituras não é um artefato matemático — é uma consequência direta de onde colocamos os partidos. E uma classe de partidos em particular faz quase toda a diferença entre as duas leituras: os partidos com escore em torno do limiar 7,0.

1.2.3 O problema do MDB: sensibilidade ao limiar de 0,01 ponto

O MDB recebe escore **7,01** na escala de Bolognesi et al. — **um centésimo acima do limiar** que separa "centro-direita" de "direita" na régua do próprio paper. É o partido mais borderline da amostra brasileira. Em 2024, Ricardo Nunes (MDB) recebeu 1,80 milhão de votos como candidato a prefeito de São Paulo — mais do que qualquer outro partido recebeu em 2020. Isso significa que a classificação do MDB **sozinha** move dramaticamente os resultados da decomposição:

Limiar C-DIR/DIR	Classe do MDB	Vereador V_entre %	Prefeito V_entre %

7,00 (Bolognesi original)	**direita**	**55,8%**	**52,3%**
7,05	centro-direita	29,8%	**8,5%**
7,10	centro-direita	29,1%	10,8%
7,20	centro-direita	29,1%	10,8%
7,50	centro-direita	34,4%	22,5%

No caso do prefeito, mover o MDB para centro-direita (limiar 7,05) faz a volatilidade entre-blocos **despencar de 52,3% para 8,5%**. É uma diferença de **44 pontos percentuais** produzida por uma única decisão binária sobre um único partido. A razão é que o MDB de Nunes concentrou cerca de 30% dos votos de prefeito em 2024 — e colocá-lo em um bloco ou outro determina quase sozinho se há realinhamento aparente ou não.

Por que isso importa? Do ponto de vista substantivo, o MDB de Ricardo Nunes em SP 2024 é herdeiro institucional direto do ciclo covista/serrista — Nunes foi vice-prefeito de Covas, assumiu o cargo com a morte de Covas em 2021, e construiu sua candidatura em 2024 como continuidade do projeto PSDB anterior, inclusive em alianças partidárias e base de apoio. Classificá-lo como "direita plena" junto com PL, NOVO e PP é uma escolha metodológica que **depende do recorte teórico de Bolognesi et al. em 2018** — escorado em survey realizado antes do ciclo Bolsonaro — e não necessariamente reflete a posição substantiva do MDB paulistano em 2024.

Consequência metodológica: ambas as leituras (tripartite e quintipartite com limiar 7,00) são defensáveis e reportamos as duas explicitamente. A leitura tripartite é mais conservadora e produz o achado "quase toda a volatilidade é intra-campo". A leitura quintipartite com limiar original é mais polarizante e produz "metade é realinhamento entre blocos". A leitura quintipartite com limiar 7,05 produz resultado quase igual à tripartite — sugerindo que **o que a Bolognesi chama de "direita" e "centro-direita" não é uma distinção empiricamente rigorosa para o voto majoritário em SP 2024**, sendo dependente de onde colocamos um único partido borderline.

Para propósitos da dissertação, o achado substantivo robusto à escolha é: **o campo esquerda+centro-esquerda tem proporção estável em 2020 e 2024 em todas as escalas** (vereador SP: 31,1% → 31,4%; prefeito SP: 43,2% → 39,0%). A oscilação mais relevante ocorre *dentro* do espaço não-esquerda — ou seja, entre candidatos e partidos que competem pelo eleitor de centro-direita/direita. A classificação exata desses partidos em subcategorias é sensível a decisões metodológicas, mas a conclusão de que **a esquerda não cresceu nem encolheu substancialmente** sobrevive a todas as escolhas testadas.

1.3 Mapa espacial da volatilidade

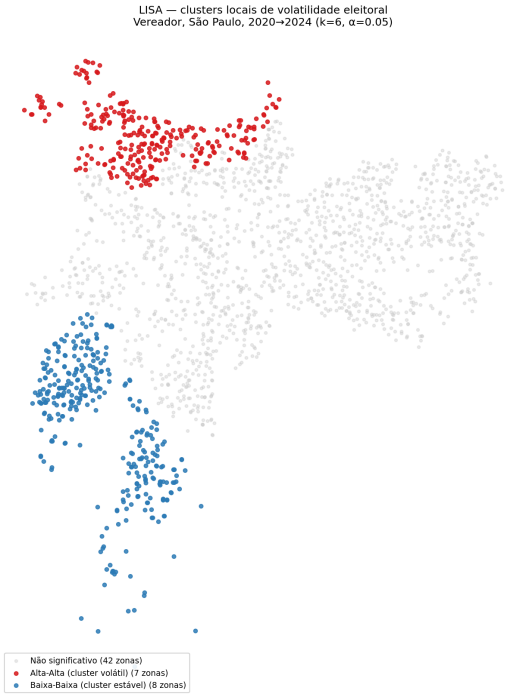

Figura 1.1 — LISA (Moran Local) da volatilidade por zona eleitoral, vereador SP 2020-2024. Moran I global = 0,42 (p = 0,001, k = 6 vizinhos, 999 permutações). Clusters HH (voláteis) na periferia norte-noroeste; clusters LL (estáveis) na periferia sul.

1.4 Mapas do espectro ideológico por zona

Enquanto a volatilidade Pedersen responde "quanto o voto mudou", o mapa do escore médio ponderado (Bolognesi et al.) responde "onde está o centro de gravidade ideológico de cada zona". Os dois mapas abaixo usam escala contínua centrada em 5,0 via *TwoSlopeNorm*, com convenção política brasileira (vermelho = esquerda, azul = direita):

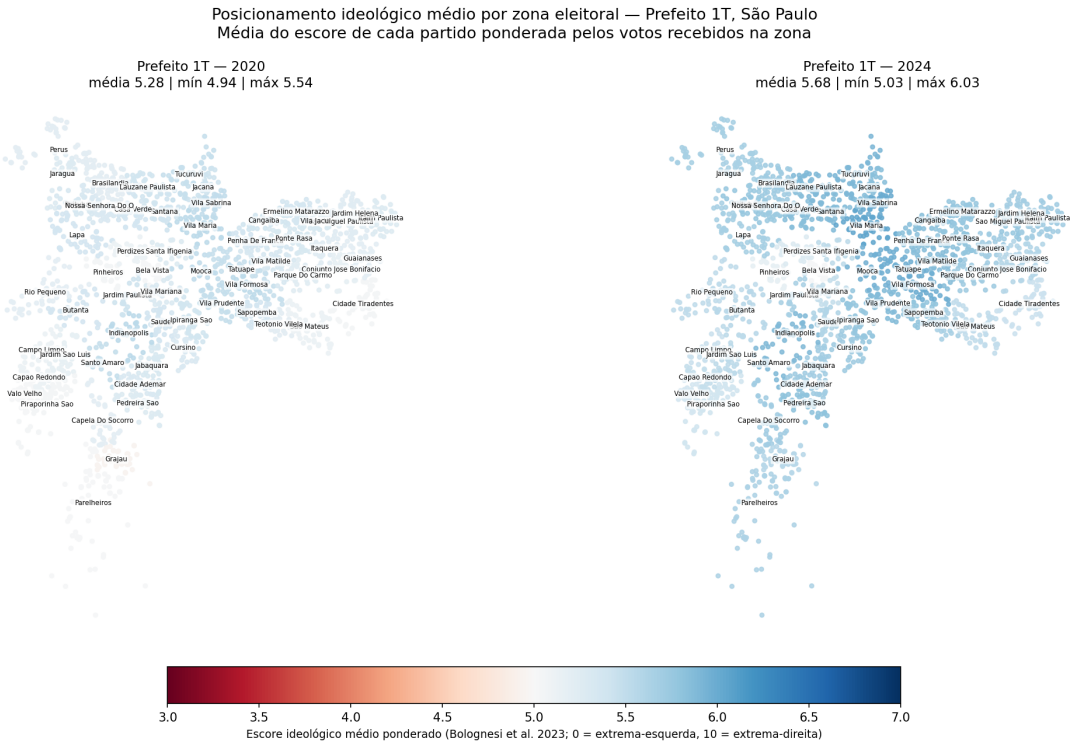

Figura 1.2 — Escore ideológico médio ponderado por voto, prefeito 1º turno, SP 2020 (esquerda) e 2024 (direita). Escala centrada em 5,0 (centro); vermelho = esquerda, azul = direita. Entre os dois painéis a cidade se desloca +0,40 pontos no eixo ideológico.

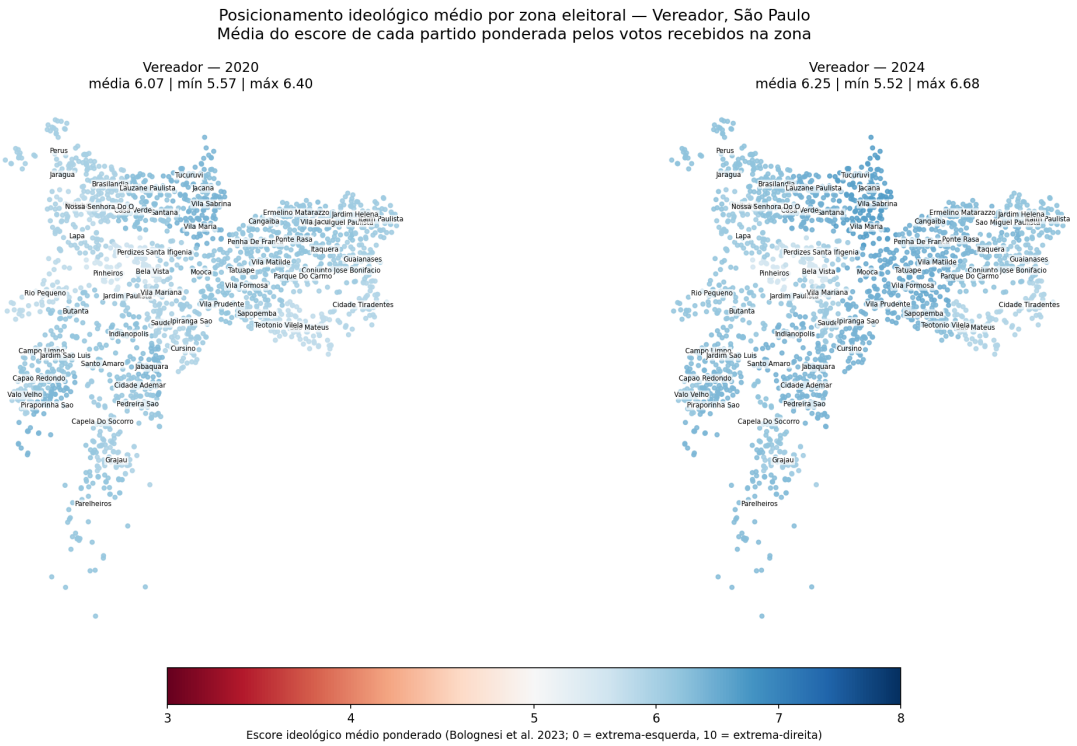

Figura 1.3 — Escore ideológico médio ponderado por voto, vereador, SP 2020 e 2024. A cidade inteira está do lado direito do centro (escore > 5) em ambos os anos, mas com gradiente visível. Bela Vista e Pinheiros (centro oeste) são as mais à esquerda da cidade nos dois ciclos.

Interpretação substantiva: o deslocamento da média da cidade entre 2020 e 2024 é **+0,40 pontos** no prefeito e **+0,19 pontos** no vereador — ambos pequenos em uma escala 0–10 mas coerentes com a narrativa de "direitização" do voto paulistano no ciclo recente. O efeito é, porém, muito mais acentuado no executivo (prefeito) do que no legislativo (vereador), refletindo a dinâmica de rotação da oferta majoritária (Covas → Nunes, emergência de Marçal) em relação à maior estabilidade da composição legislativa.

Alerta de leitura: os mapas são dominados por tons claros (próximos de 5) porque a distribuição real do voto médio ponderado entre as zonas de SP fica concentrada entre 5,0 e 6,7 — ou seja, todas as zonas da cidade ficam em alguma versão do centro ou do centro-direita na escala Bolognesi. A variação intra-cidade é relevante (até 1 ponto de escore entre zona mais à esquerda e mais à direita), mas é numericamente pequena em relação à escala 0–10 completa. Isto é consistente com o achado de 1.2: o eleitorado paulistano não transita entre campos opostos — ele se reorganiza dentro de um corredor ideológico relativamente estreito, com a variação relevante ocorrendo dentro do que Bolognesi chama de "centro-direita e direita".

Parte II — Financiamento eleitoral (2012–2024)

Evidência para H3 com dimensão material. Agenda: financiamento de campanhas, reformas políticas e recomposição da direita. Ferramental afinado com a agenda do prof. Bruno Wilhelm Speck.

2.1 Três eras regulatórias

A receita declarada pelos candidatos a vereador de SP nos quatro ciclos municipais (2012-2024) revela três eras regulatórias claramente distintas:

Ano	Total R$ mi	Partido %	PF %	PJ %	Próprio %	Era
2012	93,1	41,7	0,0	**23,8**	8,0	PJ permitida
2016	43,1	28,0	**41,0**	0,0	21,7	Pós-reforma transicional
2020	84,0	65,0	23,7	0,0	8,1	FEFC inicial
2024	**209,4**	**86,7**	9,1	0,0	2,2	FEFC consolidado

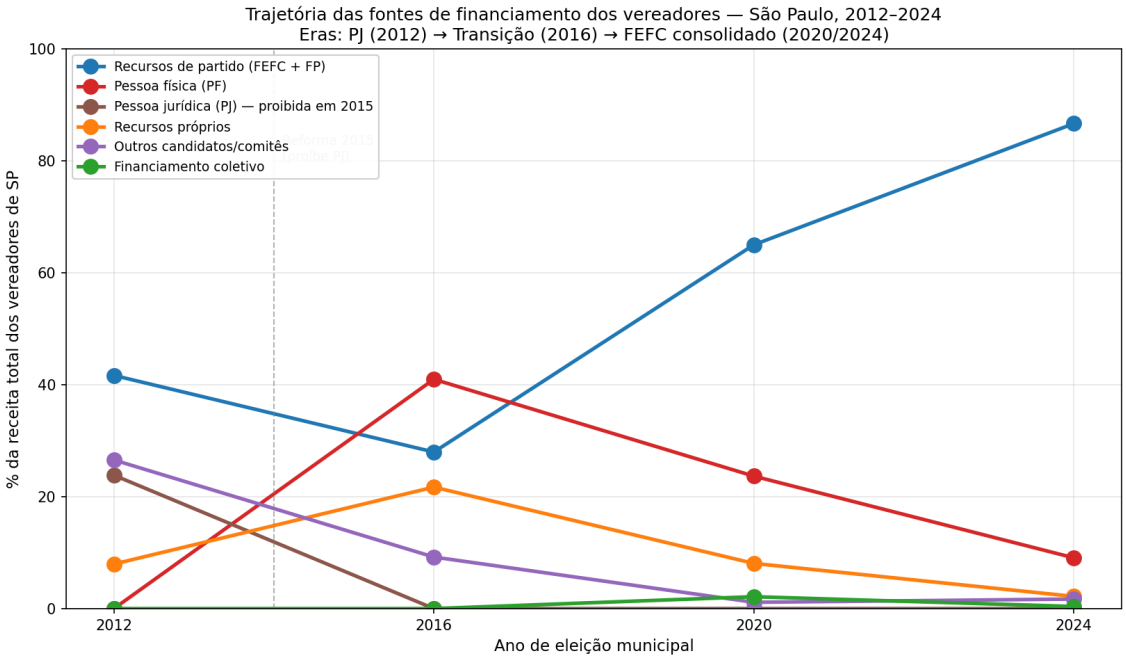

Figura 2.1 — Trajetória das fontes de financiamento dos vereadores SP em quatro ciclos municipais (2012-2024).

Em 2012, empresas como construtoras, bancos e empresas de engenharia doavam diretamente aos candidatos a vereador em SP: **R$ 22,2 milhões (24% do total)** vieram de pessoa jurídica. A reforma de 2015 proibiu esse canal. Em 2016, a reforma funcionou conforme a expectativa dos reformistas — pessoa física passou a 41% e recursos próprios a 22%, fazendo os candidatos mobilizarem diretamente seus eleitores-doadores. **Mas durou só uma eleição.**

Em 2020, o FEFC (Fundo Especial de Financiamento de Campanha) criado em 2017 começou a dominar, repassando dinheiro público aos partidos, que por sua vez o distribuem aos candidatos. Em 2024, **86,7% da receita vem de partido**, e a participação direta do

eleitor-doador (PF + crowdfunding) é apenas 9,5%. **O Fundo Especial substituiu o modelo empresarial de 2012, não o modelo de PF de 2016** — a democratização reformista foi breve e foi estatizada.

2.2 Trajetória individual por zona

Ao nível de candidato individual por zona, a transformação é ainda mais nítida. A tabela a seguir mostra a média ponderada de pessoa física, pessoa jurídica e partido dos 6 candidatos mais votados nas zonas-chave:

Zona / Ano	% PF	% Partido	% PJ	Partidos dominantes
Pinheiros 2012	0%	51%	**37%**	PSDB, PT, PPS, PV
Pinheiros 2016	**68%**	2%	0%	PT, PSDB, NOVO, Rede
Pinheiros 2020	59%	29%	0%	PT, NOVO, PSOL, PSDB
Pinheiros 2024	18%	**77%**	0%	NOVO, Rede, PT, PSOL
Indianópolis 2012	0%	43%	**46%**	PSDB, PV, PPS, PSD
Indianópolis 2016	**59%**	0%	0%	PT, PSDB, DEM, NOVO
Indianópolis 2020	57%	25%	0%	NOVO, PSD, PT, Patriota
Indianópolis 2024	10%	**88%**	0%	NOVO, PP, PL, Rede, PSOL

Dois achados desmontam narrativas correntes na literatura:

(i) O PSDB dos bairros ricos NÃO era sustentado por doador individual. A imagem canônica do tucanato paulistano — classe média progressista financiando seus candidatos — é **falsa** para vereador em 2012: 37% em Pinheiros e 46% em Indianópolis vieram de pessoa jurídica (empresarial), **zero** de pessoa física. O PSDB pré-reforma era empresarial como qualquer outro partido brasileiro da direita.

(ii) A democratização do financiamento existiu, foi breve e desapareceu. Entre 2016 e 2020, os candidatos mais votados nos bairros ricos captavam 57-68% via pessoa física. O FEFC — criado em 2017 e inflado a cada ciclo — reocupou esse espaço. Em 2024, a PF volta a ser residual (10-18%) nas mesmas zonas. **O eleitor-doador de Pinheiros existiu eleitoralmente por uma janela de 4-8 anos e foi estatizado.**

2.3 Quem eram os doadores empresariais em 2012?

A categoria "recursos de pessoa jurídica" que somou R$ 22,2 milhões para vereadores de SP em 2012 não é abstrata — é composta por 1.574 doações individuais de empresas a candidatos. A análise setorial dessas doações revela um padrão bem conhecido na literatura brasileira (Mancuso & Speck, 2015): dominância absoluta de setores ligados à infraestrutura, construção civil e serviços financeiros:

Setor econômico do doador	R$ total	N. doações
Construção de edifícios	R$ 3.791.200	75
Incorporação de empreendimentos imobiliários	R$ 1.964.500	50

Outras obras de engenharia civil	R$ 1.960.000	25
Bancos múltiplos com carteira comercial	R$ 938.500	19
Construção de rodovias e ferrovias	R$ 733.920	25
Obras de montagem industrial	R$ 715.000	5
Atividades de organizações políticas	R$ 508.080	81
Edição e impressão de cadastros	R$ 409.370	119
Comércio varejista de combustíveis	R$ 360.086	20
Serviços de engenharia	R$ 298.180	20
Vigilância e segurança privada	R$ 256.360	6

Construção civil e imobiliário somados (edifícios, incorporação, engenharia civil, rodovias, montagem industrial) respondem por R$ 9,9 milhões — 45% de todo o financiamento empresarial de vereadores em SP 2012. A participação dos bancos é de R$ 938 mil (4%). Os demais setores (combustíveis, vigilância, engenharia) são relevantes mas menores. Há uma concentração setorial notável: **construtoras financiavam a política municipal paulistana** — um padrão coerente com a intersecção entre licenciamento urbanístico, contratos de obras públicas e decisões de plano diretor no âmbito da Câmara Municipal.

No nível das empresas individualmente, os 10 maiores doadores concentravam R$ 6,1 milhões:

Empresa	R$ total doado
WTORRE ENGENHARIA E CONSTRUÇÃO S.A.	R$ 900.000
CONSTRUTORA OAS LTDA	R$ 900.000
ITAÚ UNIBANCO S.A.	R$ 838.000
UTC ENGENHARIA S/A	R$ 700.000
S.A. PAULISTA DE CONSTRUÇÕES E COMÉRCIO	R$ 545.000
CONSTRUTORA PASSARELLI LTDA	R$ 505.000
DP BARROS PAVIMENTAÇÃO E CONSTRUÇÃO	R$ 450.000
WIN WORK PINHEIROS EMPREENDIMENTO IMOBILIÁRIO	R$ 450.000
SARDENHA INCORPORAÇÃO SPE LTDA	R$ 400.000
MPC ENGENHARIA LTDA	R$ 396.000

Duas das dez maiores doadoras de vereadores de SP em 2012 — **OAS** e **UTC Engenharia** — viriam a ser citadas centralmente nos desdobramentos da Operação Lava Jato a partir de 2014, que terminaria por justificar a reforma do financiamento eleitoral de 2015. **WTorre**, **S.A. Paulista**, **Passarelli** e **MPC Engenharia** são construtoras paulistanas tradicionais, parte do tecido empresarial-político do município. **Itaú Unibanco** é o único banco no top 10 — e sua presença evidencia que o financiamento empresarial não era restrito a empreiteiras.

Relevância para a dissertação: este padrão não é surpresa na literatura (Mancuso, 2012; Mancuso & Speck, 2015; Sacchet & Speck, 2012), mas os dados individualizados por candidato em SP — cruzados com os resultados eleitorais das seções anteriores — permitem dimensionar **quanto da infraestrutura material dos vereadores do corredor das universidades vinha diretamente dessas empresas**. Em 2012, praticamente metade do financiamento dos vereadores PSDB mais votados em Pinheiros e Indianópolis era **construtora** ou **banco**. Não era "doador individual de classe média".

2.4 A trajetória dinástica: Matarazzo, Covas, Monteiro

A Parte I deste documento mostrou que Pinheiros e Indianópolis começam a série com PSDB 47–48% em 2012 e terminam com PSOL ou PL dominando em 2024. Mas essa transição partidária esconde uma história de **sucessão institucional** que vale detalhar, porque ela toca diretamente na H3 (recomposição da direita) e na discussão sobre continuidade entre o antigo "voto PSDB" e o novo "voto Novo":

Ano	Pinheiros (Z251) — top 3	Indianópolis (Z258) — top 3
2012	**Ângelo Matarazzo (PSDB)** 9.606v · Nabil Bonduki (PT) 4.742v · Floriano Pesaro (PSDB) 3.392v	**Ângelo Matarazzo (PSDB)** 11.968v · Mario Covas Neto (PSDB) 5.046v · José Alvarenga (PV) 4.907v
2016	**Eduardo Suplicy (PT)** 5.392v · Daniel Annenberg (PSDB) 2.849v · Mario Covas Neto (PSDB) 2.785v	**Eduardo Suplicy (PT)** 5.881v · Mario Covas Neto (PSDB) 5.752v · Fernando Bispo (DEM) 3.116v
2020	Eduardo Suplicy (PT) 2.324v · **Janaína Carla (NOVO)** 2.070v · Erika Silva (PSOL) 1.807v	**Janaína Carla (NOVO)** 3.322v · Felipe Becari (PSD) 2.675v · Eduardo Suplicy (PT) 2.587v
2024	**Cristina Monteiro (NOVO)** 5.552v · **Marina Bragante (Rede)** 5.286v · Nabil Bonduki (PT) 3.534v	**Cristina Monteiro (NOVO)** 6.553v · Janaína Paschoal (PP) 3.773v · Lucas Pavanato (PL) 3.535v

A trajetória em 4 atos. Em 2012, **Ângelo Andrea Matarazzo** (PSDB, sobrinho do ex-deputado Andrea Matarazzo e integrante da tradicional família de empresários paulistanos Matarazzo) é o vereador mais votado em ambas as zonas-chave, com quase 22 mil votos somados. O segundo mais votado em Indianópolis é **Mario Covas Neto** — sobrinho-neto do ex-prefeito/ex-governador Mario Covas e do então prefeito Bruno Covas. Ou seja: em 2012, **duas dinastias paulistanas tradicionais (Matarazzo e Covas) dominavam a representação de Pinheiros e Indianópolis pelo PSDB**, em forma quase literal de continuidade familiar-partidária.

Em 2016, já aparece o primeiro sinal de reorganização: **Eduardo Matarazzo Suplicy (PT)**, senador histórico do PT e ele próprio herdeiro da família Matarazzo por lado materno, entra na disputa de vereador como estratégia simbólica do PT para "reocupar" os bairros ricos. Suplicy vence em Pinheiros (5.392 votos) e Indianópolis (5.881 votos), derrotando os candidatos do PSDB. O PSDB mantém presença via Daniel Annenberg e, curiosamente, Mario Covas Neto em ambas as zonas — mas em posições secundárias.

Em 2020, acontece a primeira aparição no topo de **Janaína Carla de Lima**, candidata do NOVO com captação **99% pessoa física** e perfil de "renovação liberal jovem". Ela assume a 2ª posição em Pinheiros e a 1ª em Indianópolis. O PSDB não aparece mais no top 3 em nenhuma das zonas. Suplicy (PT) ainda está presente mas cai de posição. O PSOL entra com Erika Silva em Pinheiros — primeira aparição no top 3 da zona.

Em 2024, a transição se consolida. **Cristina Monteiro (NOVO)** — ex-PSDB, migrou para o Novo em 2018, vereadora atual em seu segundo mandato — é a mais votada em ambas as zonas, com 12.105 votos somados. **Marina Bragante (Rede)**, psicóloga, é a 2ª em Pinheiros. O PT sobrevive pela figura de **Nabil Bonduki** — professor titular da FAU-USP, arquiteto-urbanista — que é a mesma pessoa que apareceu no top 3 de Pinheiros em 2012. Bonduki é o elo simbólico de continuidade do PT em Pinheiros ao longo dos 12 anos, embora agora ocupando posição secundária.

O significado substantivo da transição Matarazzo → Monteiro: o voto do eleitor "rico tradicional" (Jardim Paulista, Indianópolis, Pinheiros) manteve — em termos de perfil sociológico e de quem ele é — um **padrão de continuidade**. Mudaram os nomes dos candidatos e mudou o partido carregador (PSDB → NOVO), mas a estrutura de representação institucional preservada é reconhecível: candidata-celebridade de direita-liberal cosmopolita (Cristina Monteiro hoje, Ângelo Matarazzo em 2012) com voto concentrado nos mesmos locais de votação. O caso análogo no Executivo é **Ricardo Nunes (MDB)** — vice-prefeito de Bruno Covas, assumiu com sua morte em 2021, elege-se em 2024: continuidade institucional quase literal do ciclo Covas, por dentro de um partido diferente. A reorganização partidária é **cosmética** no sentido de que as *pessoas* e as *famílias* que exerciam a representação política dos bairros ricos em 2012 (ou seus herdeiros institucionais diretos) continuam exercendo em 2024 — só que agora via legendas diferentes.

2.5 Implicações para a H3 do projeto

A Hipótese 3 afirmava que *"o recrutamento e as disputas intrapartidárias da centro-direita ao longo do tempo influenciaram o novo comportamento eleitoral marcado pela contestação. Destarte, a centro-direita foi atraída pelo campo da direita e extrema-direita"*. Os achados das seções 2.1–2.4 permitem reformular a hipótese com maior precisão empírica:

A centro-direita brasileira pós-2020 é uma fase específica no ciclo regulatório do financiamento, não um movimento autônomo do eleitorado. O PSDB de SP perde base em quatro dimensões simultâneas: (a) *eleitoral*, via colapso do voto de vereador e prefeito; (b) *institucional*, via migração de quadros para Novo, MDB e PL; (c) *material*, via perda da infraestrutura de financiamento empresarial (PJ proibida em 2015) sem reconstrução do canal pessoa física (reocupado pelo FEFC em 2020-2024); (d) *simbólica*, via substituição das dinastias familiares tradicionais (Matarazzo, Covas) por candidatos-celebridade de perfil liberal cosmopolita vinculados ao Novo ou ao próprio MDB.

Mas — e isto é central — a H3 na formulação original parece sugerir que a centro-direita foi "absorvida" pela direita pura e dura. Os dados mostram algo mais sutil: a centro-direita paulistana da era Covas/Serra foi absorvida em partes por diferentes destinos. Parte migrou para o Novo (voto "renovação liberal" que capta PF ativamente — Cristina Monteiro, Janaína Carla). Parte para o MDB de Nunes (continuidade institucional direta do ciclo Covas, via sucessor indicado). Parte para o PL/PP (voto conservador duro, captação 100% FEFC). O "ataque à direita" existe, mas é uma dispersão — não uma absorção unilateral. O colapso do PSDB é real; a reorganização da oferta partidária ocorre em **múltiplas direções simultâneas**.

Parte III — Sociologia urbana institucional

Evidência para H4. Agenda: ecologia eleitoral, sociologia urbana, ambientes institucionais. Ferramental afinado com a agenda do prof. Eduardo Marques (FLS 6195 — Cidades, Governo e Políticas Públicas) e dialogando com a escola paulistana de sociologia urbana (Marques, Torres et al., Torres, Bichir).

3.0 Moldura teórica: a escola paulistana e o ambiente institucional

A agenda de pesquisa sobre estratificação socioeconômica do espaço metropolitano de São Paulo, consolidada no grupo Marques–Torres–Bichir (ver Marques, 2015; Torres, Marques, Ferreira & Bichir, 2003; Marques, Scalon & Oliveira, 2018), estabeleceu três teses empíricas que moldam este capítulo:

(i) A hierarquia socioeconômica intra-metropolitana de SP é extraordinariamente estável no tempo. Torres et al. (2003), usando dados de 1991 e 2000, mostram que os bairros de alta renda do centro-oeste paulistano (Pinheiros, Jardim Paulista, Itaim, Vila Olímpia, Morumbi) mantêm sua posição relativa no ranking de renda há décadas. Marques (2015) estende esse argumento até os anos 2010, mostrando que a segregação por renda é um atributo quase invariante da estrutura urbana paulistana. Isso é o que justifica usar dados do Censo 2010 como proxy razoável para a posição relativa das zonas em 2024 — um argumento metodológico desenvolvido em detalhe na seção 9.1.

(ii) Mas a segregação de renda não é a única dimensão relevante do espaço urbano. Marques (2015) argumenta que, além do gradiente de renda, a cidade se estrutura por *redes de equipamentos e instituições* — serviços públicos, escolas, universidades, centros culturais — cuja distribuição territorial é **independente** da distribuição de renda em muitos casos. Um bairro de renda alta pode ter alta ou baixa densidade institucional; um bairro de renda média pode ter equipamentos de prestígio cultural. A tese é que **o efeito político-territorial do espaço urbano não vem só da renda dos moradores — vem também do que o ambiente institucional oferece**.

(iii) Ambientes institucionais educativo-culturais funcionam como infraestrutura de socialização política. Marques (2015) e Hoyler, Gelape & Silotto (2021) argumentam, seguindo uma tradição mais ampla que vai de Tocqueville a Putnam, que frequentar ambientes educativos-culturais específicos (universidades, escolas construtivistas, centros culturais) produz **vínculos político-territoriais específicos** — tanto de identificação quanto de mobilização. Esta tese, entretanto, raramente foi testada quantitativamente no contexto paulistano. Este capítulo faz exatamente isso: operacionaliza a hipótese do ambiente institucional como preditor do voto e a compara empiricamente com a hipótese alternativa (renda/classe).

A ponte com Inglehart & Norris. A agenda da escola paulistana tem, neste capítulo, uma conexão inesperada com a literatura internacional recente sobre clivagem cultural no voto contemporâneo (Inglehart & Norris, 2016, 2019). Se Marques argumenta que o ambiente institucional é uma dimensão independente da segregação urbana, Inglehart & Norris argumentam que a educação e o cosmopolitismo — produzidos justamente pelos ambientes institucionais — tornam-se progressivamente o eixo organizador do voto em democracias contemporâneas. As duas tradições se encontram na hipótese empiricamente testável: **na SP**

pós-2016, a presença de ambiente institucional educativo-cultural explica o voto melhor do que a renda.

3.1 Renda não explica o voto ideológico em SP 2024

Cruzamos renda per capita dos setores censitários (Censo 2010) com o escore ideológico médio ponderado por zona (2024). Pipeline: 18.953 setores censitários de SP via geobr × 2.061 locais de votação do CEM via spatial join × agregação por zona eleitoral. Para a limitação temporal do Censo 2010, veja seção 5 adiante.

A correlação renda × escore ideológico é NEGATIVA em SP 2024:

Eleição	r (Pearson)	R^2	Direção
Vereador 2024	**-0,297**	0,088	renda alta → escore menor (mais à esquerda)
Prefeito 1T 2024	**-0,166**	0,028	mesma direção, efeito menor
Vereador 2020	**-0,211**	0,045	padrão consistente no tempo

Renda explica menos de 9% da variância ideológica entre zonas. Mais de 91% não é explicada por renda. O sinal é **oposto** ao voto de classe clássico — zonas mais ricas votam mais à esquerda, não menos. Mas o efeito é fraco.

3.2 O índice institucional cultural-progressista

A hipótese alternativa é que o fator explicativo é **ambiente institucional educativo-cultural**, não renda. Operacionalizamos essa hipótese construindo um índice de "densidade institucional cultural-progressista" por zona, identificando locais de votação em quatro categorias:

(i) Universidades (USP, Mackenzie, PUC, Uninove, FAAP, FMU, Insper, Senac, Senai, Fatec, etc.); **(ii) Escolas particulares progressistas** (Vera Cruz, Equipe, Lumiar, Oswald de Andrade, Stella Maris, Escola da Vila, Horizontes, Itaca); **(iii) Escolas públicas de prestígio cultural** (Caetano de Campos, Fernão Dias Paes, Godofredo Furtado, Amorim Lima, Clorinda Danti, Fidelino de Figueiredo); **(iv) Instituições culturais internacionais** (Goethe-Institut, Alliance Française, Dante Alighieri, Cervantes). O índice final é a fração de locais da zona em pelo menos uma categoria.

Resultado: a correlação com o escore ideológico é r = –0,661, explicando 43,7% da variância — cinco vezes mais que a renda.

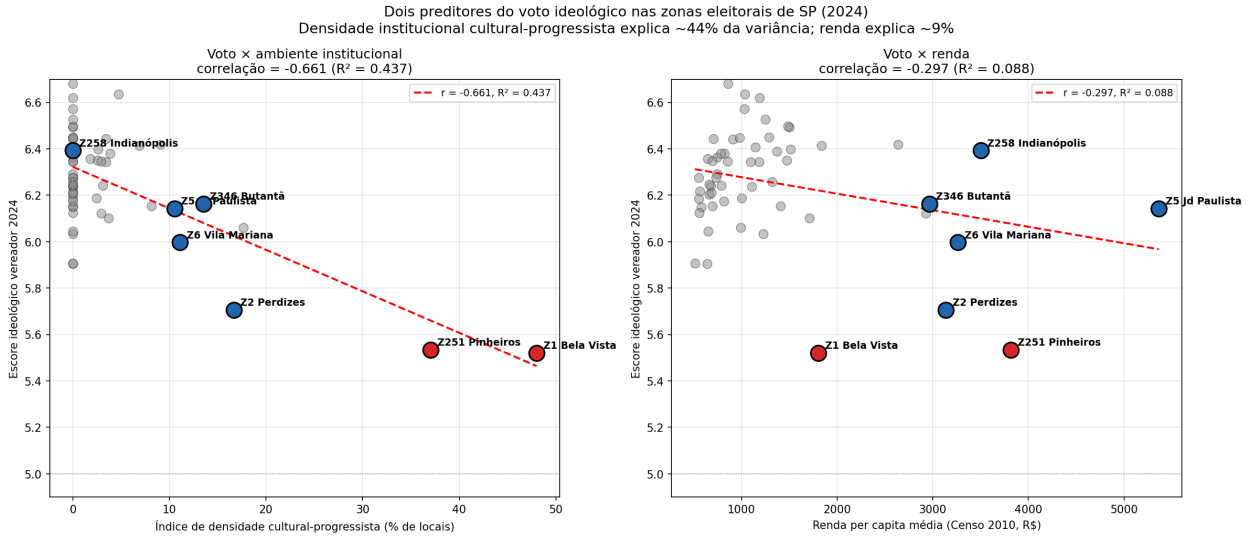

Figura 3.1 — Comparação direta: índice institucional (esquerda, $R^2 = 0{,}437$) vs renda per capita (direita, $R^2 = 0{,}088$) como preditores do escore ideológico de vereador 2024 por zona.

3.2.1 Os locais específicos que compõem o índice

Para dar concretude aos números, vale enumerar exatamente quais locais de votação compõem o índice institucional nas zonas mais relevantes:

Bela Vista (Z1) — 48,0% dos locais são categorizados, o maior índice da cidade. A zona tem 25 locais, dos quais 11 são universitários (!): Mackenzie em múltiplos prédios (Consolação, Itambé, Prédio 45, Prédio 09), PUC-SP Consolação, PUC-SP Ciências Exatas, FMU, Senac Consolação, Faculdade Phorte, Uniban, Uninove Paulista. Adicionalmente, a EE Caetano de Campos (histórica escola pública paulistana, em seu prédio tradicional na Consolação) entra como prestígio público. É o caso mais extremo da "concentração educativo-cultural" em uma única zona: **quase metade dos locais de votação de Bela Vista são campus universitários ou escolas públicas tradicionais**.

Pinheiros (Z251) — 37,0% dos locais, segundo maior índice da cidade. A zona tem 27 locais, distribuídos de forma muito mais diversificada que Bela Vista:

Categoria	N	Locais específicos
Universidade	1	Uninove Pinheiros
Escola progressista	4	Colégio Vera Cruz, Escola Lumiar, Escola Oswald de Andrade, Colégio Horizontes
Prestígio público	3	EE Fernão Dias Paes, EE Godofredo Furtado, EE Antonio Alves Cruz
Internacional cultural	2	Goethe-Institut, Colégio Stella Maris

A lista acima é politicamente reveladora. **Colégio Vera Cruz, Escola Lumiar, Escola Oswald de Andrade** e **Colégio Horizontes** são as quatro escolas particulares historicamente associadas à pedagogia construtivista/progressista de classe média alta paulistana. Seu público-alvo é bem definido: filhos de profissionais liberais, acadêmicos, jornalistas, artistas, advogados — exatamente o perfil do "cosmopolitismo educado" que Inglehart & Norris descrevem. **EE Fernão Dias Paes** e **EE Godofredo Furtado** são escolas estaduais de prestígio histórico na região, frequentadas por filhos de servidores públicos e professores da rede. **Goethe-Institut** é o centro cultural alemão — ponto focal da cena cosmopolita paulistana. Somados, esses locais capturam boa parte do que se entende, na sociologia

urbana paulistana, como "ambiente cultural progressista de Pinheiros".

Indianópolis (Z258) — 0,0% dos locais, o menor índice da cidade. A zona tem 31 locais de votação, e nenhum deles é categorizado em nossa lista. Não há universidades, não há escolas particulares progressistas de tradição reconhecida, não há escolas públicas de prestígio cultural nacional, e não há instituições culturais internacionais. Os locais de votação de Indianópolis são **escolas estaduais e municipais regulares, colégios particulares de bairro e centros comunitários** — instituições de ensino que servem a população local em sua vida cotidiana, mas sem a dimensão de prestígio cultural-intelectual que marca os locais de Pinheiros e Bela Vista. Isto é substantivamente notável: a renda per capita de Indianópolis é praticamente idêntica à de Pinheiros (R$ 3.504 vs R$ 3.819), mas o perfil institucional do território é **radicalmente diferente**. É um bairro rico *residencial* — sem grande infraestrutura cultural-universitária pública ou privada. Essa **diferença territorial em dimensão ortogonal à renda** é exatamente o que Marques (2015) prevê quando argumenta que a distribuição de equipamentos institucionais é parcialmente independente da distribuição de renda.

3.2.2 O mecanismo: como o ambiente "fala" politicamente?

Identificado o sinal correlacional forte ($r = -0{,}66$), resta perguntar **por que** o ambiente institucional produziria voto mais à esquerda. Quatro mecanismos plausíveis, compatíveis com a literatura:

(a) Mecanismo de composição populacional. A versão mais "bruta": universidades, escolas construtivistas e instituições culturais atraem **moradores** com perfil específico (professores, estudantes, funcionários administrativos, artistas). O voto da zona reflete esse perfil moradores — não um efeito do ambiente em si. Nesse caso, ambiente é proxy de composição demográfica específica.

(b) Mecanismo de socialização política. Frequentar ambientes universitários ou escolas progressistas produz exposição a valores, debates e normas políticas específicas (pós-materialismo, cosmopolitismo, tolerância ao pluralismo, etc.). Ao longo de anos de convivência, o eleitor internaliza parcialmente esses valores e os traduz em escolha eleitoral. Essa é a formulação clássica de Inglehart & Norris (2019) para democracias contemporâneas.

(c) Mecanismo de rede e mobilização. Universidades e escolas de elite cultural são também **lócus de recrutamento político**: alunos e professores se engajam em campanhas, formam grupos de apoio, distribuem materiais, organizam debates. O ambiente institucional cria redes de ativismo que se expressam eleitoralmente nas proximidades. Essa é a leitura de Hoyler, Gelape & Silotto (2021) sobre construção de vínculos político-territoriais em SP.

(d) Mecanismo de identidade cultural deflagrado. Após choques políticos nacionais (impeachment 2016, eleição Bolsonaro 2018), a identidade cultural-cosmopolita que ambientes universitários sempre produziram torna-se **politicamente saliente**. A variável que antes era latente (ser universitário em Pinheiros não distinguia seu voto) torna-se mobilizada (ser universitário em Pinheiros implica se opor ao bolsonarismo). Este mecanismo é o que explica melhor o achado da seção 3.6 (teste temporal): a correlação entre índice e voto **cresce** ao longo do tempo, consistente com ativação recente.

Os quatro mecanismos não são mutuamente exclusivos e provavelmente operam simultaneamente. **A dissertação não consegue, com os dados atuais, distinguir definitivamente entre eles.** Mas a combinação de evidências do teste temporal (3.6) com o

padrão de candidatos (Parte IV) sugere que (d) + (c) são os mecanismos dominantes — o ambiente institucional funciona como *lócus de coordenação política recente*, não como atributo estrutural antigo. A hipótese (a), de composição, não poderia explicar por que o sinal era nulo em 2016 e emergiu em 2020 — a composição populacional das zonas muda devagar demais.

3.3 O caso Pinheiros × Indianópolis

Pinheiros (Z251) e Indianópolis (Z258) são empates em renda (R$ 3.819 vs R$ 3.504 per capita, 2ª e 3ª da cidade) mas polos opostos em ambiente institucional:

Indicador	Pinheiros (Z251)	Indianópolis (Z258)
Renda per capita média (2010)	R$ 3.819 (2º)	R$ 3.504 (3º)
Índice institucional	**37,0%**	**0%**
Universidades	1	0
Escolas progressistas	4	0
Prestígio público	3	0
Internacional cultural	2 (Goethe!)	0
Escore ideológico vereador 2024	**5,53**	**6,39**
PSDB em 2012 (vereador)	48%	47%
Partido #1 em 2024 (vereador)	PSOL 28%	PL 20%

A diferença ideológica (0,86 pontos de escore) é quase exatamente o que o modelo prevê a partir da diferença de densidade institucional (48 pp × 0,019 = 0,91). **Pinheiros e Indianópolis são empates em renda e polos opostos em instituições E em voto.** A variável diferenciadora é institucional, não econômica.

3.4 Regressão multivariada

Em OLS com renda e índice institucional como preditores simultâneos do escore de vereador 2024 (n = 57 zonas):

Modelo	Variáveis	R^2	β renda	β índice
1	só renda	0,088	negativo	—
2	só índice institucional	**0,437**	—	**-0,0185**
3	renda + índice	0,439	+0,000011 (desprezível)	-0,0185

O R^2 adicional que renda acrescenta após controlar pelo índice institucional é 0,002 — **praticamente zero**. Controlando pela densidade institucional, a renda perde todo o poder explicativo. O coeficiente do índice é robusto: cada ponto percentual reduz o escore em 0,019 — suficiente para produzir a diferença de ~0,9 pontos entre Bela Vista/Pinheiros e Indianópolis.

3.5 Robustez

Cinco testes de robustez aplicados ao achado: **(a) leave-one-category-out** — todas as variantes do índice preservam $R^2 > 0,29$; **(b) cada categoria isolada** — prestígio público sozinho tem r = –0,624 apesar de aparecer em só 6 zonas; **(c) bootstrap IC 95%** — [–0,816; –0,223] para vereador 2024, [–0,783; –0,144] para prefeito, [–0,690; –0,033] para vereador 2020, todos excluindo zero; **(d) controle por densidade urbana** (n de locais da zona) — n_locais sozinho tem $R^2 = 0,003$, não é confundidor; **(e) variável dependente alternativa** (% de seções com esquerda majoritária por plurality bipartite): a correlação do índice sobe para **r = +0,814, R^2 = 0,663**, enquanto a da renda fica em r = +0,079. O índice explica 66% da variância numa métrica eleitoral mais direta.

3.6 O teste temporal — achado mais surpreendente

Mantendo o índice fixo (base CEM/USP 2022) e variando o voto, a correlação entre índice e escore ideológico **não é estável** — ela **cresce** ao longo dos ciclos:

Ano	Vereador r (R^2)	Prefeito 1T r (R^2)
2016	**+0,108 (0,012)**	**-0,012 (0,000)**
2020	-0,500 (0,250)	-0,249 (0,062)
2024	**-0,661 (0,437)**	**-0,600 (0,360)**

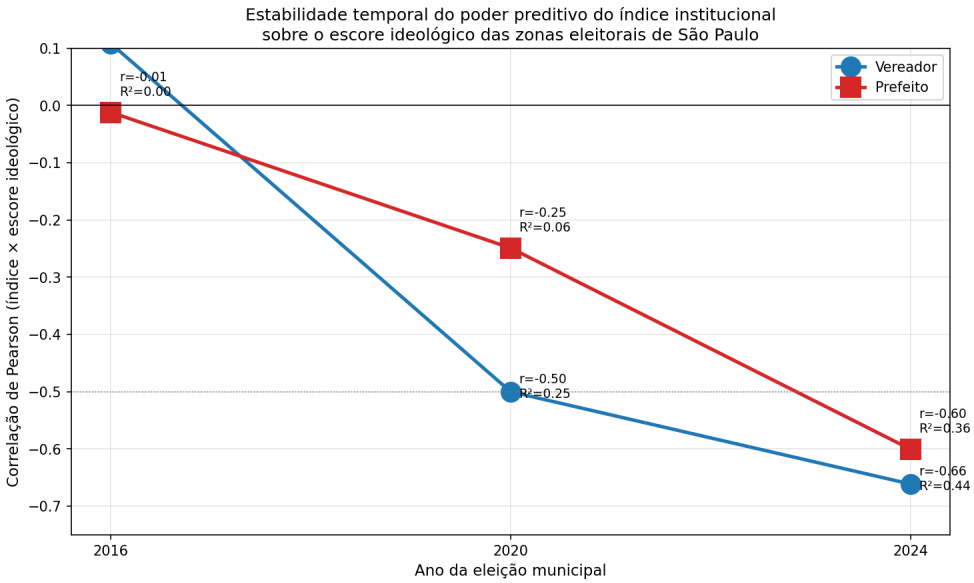

Figura 3.2 — Estabilidade temporal do poder preditivo do índice institucional sobre o escore ideológico por zona eleitoral, SP 2016-2024.

Em 2016, o índice explicava ZERO do voto. As universidades, escolas progressistas e instituições culturais existiam exatamente nas mesmas zonas, mas não se traduziam em diferenciação política. A correlação emerge em 2020 (r = –0,50) e se consolida em 2024 (r = –0,66).

Interpretação (compatível com Inglehart & Norris, 2016, 2019): o ambiente institucional cultural-progressista foi **politicamente ativado** entre 2016 e 2020. As "infraestruturas" (escolas, universidades, instituições) sempre existiram; o que mudou foi que, após o choque do impeachment (2016), a eleição de Bolsonaro (2018) e a polarização Lula-Bolsonaro (2022),

passaram a "falar" politicamente — a mediar uma identidade cultural-cosmopolita que se tornou saliente no voto. É exatamente o mecanismo descrito por Inglehart & Norris para democracias ocidentais contemporâneas: a clivagem cultural substitui gradualmente a clivagem econômica como organizador do voto, ativada por choques políticos específicos.

Esse achado reforça, não enfraquece, a tese central. Uma hipótese puramente estrutural ("renda alta explica voto") teria produzido correlações estáveis no tempo. A hipótese institucional-cultural prevê exatamente o padrão observado — ativação emergente após choques políticos específicos.

Parte IV — Perfil dos candidatos

Complemento sociológico aos três eixos. Analisa a correspondência entre oferta partidária (candidato) e demanda eleitoral (zona) via metadados de ocupação e partido. Esta parte conecta diretamente com os mecanismos (c) e (d) discutidos em 3.2.2 — se o ambiente institucional funciona como lócus de mobilização política, ele também é lócus de produção de candidatos.

4.1 O tipo de candidato que emerge espelha o eleitorado

Para cada um dos 547 candidatos a vereador em SP 2024 com mais de 500 votos, calculamos a porcentagem do seu voto que vem de zonas com alta densidade institucional (índice > 15%) e classificamos sua ocupação declarada (via TSE consulta_cand) em categorias temáticas. O resultado é uma diferenciação dramática entre candidatos "territorialmente periféricos" e candidatos "territorialmente culturais":

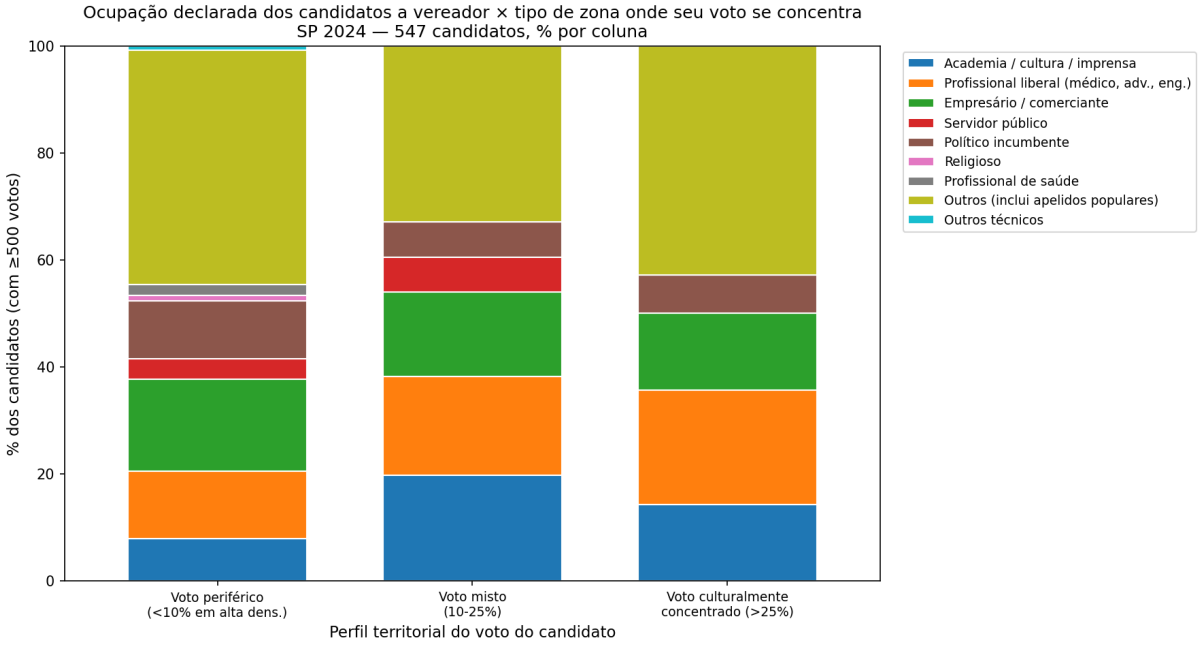

Figura 4.1 — Distribuição de categoria ocupacional dos candidatos a vereador SP 2024 (≥500 votos), por perfil territorial do voto. Academia/cultura/imprensa triplica entre voto periférico (7,9%) e voto misto (19,7%). Profissional liberal cresce de 12,7% para 21,4%.

Categoria de ocupação	Voto periférico (<10%)	Voto misto (10-25%)	Voto cultural (>25%)
Academia / cultura / imprensa	7,9%	**19,7%**	14,3%
Profissional liberal (médico, adv.)	12,7%	18,4%	**21,4%**
Empresário / comerciante	17,1%	15,8%	14,3%
Servidor público	3,9%	6,6%	0,0%
Político incumbente	10,7%	6,6%	7,1%
Religioso	1,1%	0,0%	0,0%

Outros (inclui apelidos populares)	**43,8%**	32,9%	42,9%

Três padrões emergem da tabela: **(i)** a categoria *academia, cultura e imprensa* triplica entre candidatos com voto periférico e candidatos com voto misto (7,9% → 19,7%), confirmando que o ambiente institucional cultural produz candidatos, não só eleitores; **(ii)** a categoria *profissional liberal* (médicos, advogados, engenheiros, arquitetos) cresce linearmente conforme o voto se concentra em zonas densas (12,7% → 18,4% → 21,4%); **(iii)** a categoria *religioso* desaparece completamente nas zonas culturais — não há pastores, padres ou bispos no topo eleitoral dessas zonas. A categoria "outros" é dominada por **apelidos populares de bairro** na periferia, o que pulveriza a classificação mas revela um padrão qualitativo distinto.

4.2 Os candidatos territorialmente culturais — lista nominal

Com perfis por categoria estabelecidos, vale nomear os candidatos concretos que aparecem no topo dos dois perfis territoriais. A tabela abaixo lista os 10 candidatos com maior percentual de votos concentrados em zonas de alta densidade institucional (Pinheiros, Bela Vista, Perdizes, Vila Mariana, Butantã), entre candidatos com pelo menos 500 votos no total:

%	Candidato	Partido	Ocupação	Total votos
43,1	Dr. David Zylbergeld Neto	PL	Médico	999
42,5	Henry Kadima	PL	Empresário	2.002
40,9	Neti Araújo	PT	—	1.954
39,5	Leandro Mofsovich	NOVO	Empresário	1.390
34,3	Veronica Bilyk	PSB	Publicitária	3.369
33,5	Carmen Silva	PSB	—	9.781
33,4	Eduardo Dourado	PRD	Advogado	806
28,1	Marcão do Esporte	PV	—	569
27,5	**Marina Bragante**	Rede	Psicóloga	**39.147**
26,3	**Claudia Visoni**	PV	Jornalista	**6.006**
26,2	**Cristina Monteiro**	NOVO	Vereadora	**56.904**
25,7	Sidney Stahl	NOVO	Advogado	716
25,0	Takeda	PRD	Advogado	801

Observações: Marina Bragante (Rede, psicóloga) é a candidata com maior volume absoluto (39.147 votos) entre aqueles com concentração territorial cultural alta. Cristina Monteiro (NOVO, vereadora) tem 56.904 votos — é de longe a mais votada da categoria e, como discutido na Parte II.4, é a herdeira institucional do voto Matarazzo/Covas via migração PSDB→NOVO. Claudia Visoni (PV, jornalista) é outro exemplo paradigmático — vem da cena ambientalista-urbana paulistana e capta voto de perfil educado-progressista. Dois dos quatro médicos e três dos quatro advogados no top 13 são do **PL ou PRD**, sugerindo que a correspondência ocupação × ideologia não é unívoca: há "profissional liberal de direita" tanto quanto "profissional liberal de esquerda", e ambos competem pelo mesmo eleitorado educado.

É também notável a **ausência** de alguns perfis esperados na lista. Não há professores universitários famosos (exceto Nabil Bonduki, que aparece um pouco abaixo do corte com 24%). Não há políticos incumbentes de carreira longa — o topo é dominado por **candidatos de primeira ou segunda geração de visibilidade pública**, não por ocupantes estabelecidos. Esse padrão é coerente com a tese de ativação recente do ambiente institucional: os candidatos que captam esse voto emergiram nos últimos ciclos, não são fósseis da representação paulistana tradicional.

4.3 Os candidatos territorialmente periféricos — lista nominal

A simetria inversa: os 15 candidatos com maior porcentagem de votos vindos **exclusivamente** de zonas de baixa densidade institucional (praticamente 100%):

% baixa	Candidato	Partido	Ocupação
100,0	Roni da Limpeza	PSD	Empresário
99,9	Fernando Manso	PRD	Cabeleireiro e barbeiro
99,9	Alemão do Conselho	União	—
99,8	Coletivo Pastora Lilian Alves	Republicanos	Comerciante
99,8	Negro Edson	Solidariedade	—
99,8	Eliel Alves	Pode	Técnico de enfermagem
99,8	Miltão	PT	—
99,7	Anadethy Caravanista	MDB	Pedagoga
99,7	Gil do Celular	PRD	Comerciante
99,7	Tio Waltinho	Avante	Comerciante
99,7	Professor Alves	PRD	Professor
99,6	Yes da ZL	Solidariedade	Motorista particular
99,6	Kéké Espetinhos	Pode	Empresário
99,6	Mallu Mattos	União	—
99,6	Natal Líder Comunitário	PSB	Empresário

Três padrões visíveis. Primeiro, os nomes de urna: *Roni da Limpeza, Fernando Manso "cabeleireiro", Alemão do Conselho, Pastora Lilian, Gil do Celular, Tio Waltinho, Kéké Espetinhos, Yes da ZL, Natal Líder Comunitário*. São apelidos que indicam **origem profissional local** (cabeleireiro, motorista, comerciante), função comunitária (conselheiro, pastora, líder comunitário) ou marcador territorial ("da ZL" = Zona Leste). Nenhum desses padrões aparece entre os candidatos territorialmente culturais.

Segundo, a ocupação. A maioria são **empresários de pequeno porte** (Roni, Natal, Kéké — donos de estabelecimentos locais), **comerciantes** (Gil, Tio Waltinho), **prestadores de serviço** (Fernando Manso, Yes da ZL), **técnicos de nível médio** (Eliel Alves, Professor Alves), e **pastores evangélicos** (Pastora Lilian). É o perfil clássico do "vereador de bairro" descrito por Almeida & Carneiro (2003): figura conhecida localmente, com vínculo direto e cotidiano com o

eleitor.

Terceiro, os partidos. A distribuição atravessa ideologias: **PSD, PRD, União, Republicanos, Solidariedade, Pode, MDB, PT, Avante, PSB** — praticamente todos os partidos com estrutura nacional aparecem. Isso confirma que o "vereador de bairro periférico" é uma **categoria sociológica** antes de ser uma categoria ideológica: existem candidatos progressistas e candidatos conservadores competindo pelo mesmo espaço, com a mesma forma de vínculo territorial-comunitário. O que os une não é o programa político — é o tipo de relação social com o eleitorado.

4.4 A tese da dupla produção: ambiente institucional produz eleitor e candidato

Se juntarmos os achados das Partes III e IV, emerge uma tese mais forte e teoricamente articulada do que a hipótese original do projeto (H4). A H4 dizia que "o voto de esquerda nos bairros ricos aponta para outras variáveis independentes do que a renda ou a escolaridade". O achado deste rascunho é mais específico: **o ambiente institucional cultural-progressista produz simultaneamente eleitores de perfil específico E candidatos de perfil espelho**, e a relação entre os dois é reforçada pela ativação política recente.

O mecanismo dual funciona assim: (i) universidades, escolas construtivistas, instituições culturais internacionais produzem **eleitores** com repertório cultural-cosmopolita específico, acumulado ao longo dos anos de convivência no ambiente; (ii) os mesmos ambientes produzem **candidatos** — psicólogos, jornalistas, publicitários, advogados de nicho, profissionais ligados a ONGs, academia, imprensa — que partilham o repertório cultural dos eleitores; (iii) após o choque político 2016–2018, essa correspondência latente se ativa como identidade política saliente, e ambos os lados convergem na produção de um circuito de representação territorial coeso; (iv) nas zonas sem infraestrutura institucional — mesmo em renda equivalente — nem eleitores nem candidatos desse perfil são produzidos, e o voto segue lógicas distintas (clientelista, religiosa, personalista de bairro).

Dois circuitos paralelos de representação política operam na mesma cidade de São Paulo: um **circuito institucional-cultural**, produzindo eleitores progressistas educados e candidatos profissionais liberais de nicho, concentrado no corredor das universidades; e um **circuito comunitário-personalista**, produzindo eleitores de base local e candidatos com apelidos de bairro, distribuído pela periferia e por zonas sem densidade institucional significativa. A oposição entre os dois não é primariamente ideológica (há progressistas e conservadores em ambos), é **sociologicamente estrutural** — a forma da relação candidato-eleitor é distinta. E a única variável que distingue empiricamente de onde cada circuito emerge é o **ambiente institucional**.

Isto é o argumento substantivo central da dissertação que emerge desta análise. Não é uma tese sobre ideologia — é uma tese sobre como *ambientes institucionais produzem representação política*. A H4 original, formulada como "o voto de esquerda nos bairros ricos aponta para outras variáveis", é um caso particular desta tese mais geral: o voto progressista nos bairros ricos aponta para ambiente institucional, e o ambiente institucional produz candidatos espelho que ativam esse voto. A reciprocidade é o mecanismo.

Parte V — Convergência temporal e síntese

5.1 Os três eixos se ativam simultaneamente

Um achado colateral importante deste trabalho é que as transformações identificadas nos três eixos empíricos ocorrem **no mesmo período histórico** — entre 2016 e 2020 — e consolidam-se em 2024. A simultaneidade sugere um mecanismo comum subjacente:

Eixo	Indicador	2012	2016	2020	2024
Sistema partidário	PSDB % vereador Pinheiros	48%	36%	18%	~0%
	PSOL % vereador Pinheiros	—	12%	**28%**	**28%**
Financiamento	% PF média dos top-6 Pinheiros	0%	**68%**	59%	18%
	% Partido média dos top-6 Pinheiros	51%	2%	29%	**77%**
Sociologia urbana	R^2 índice institucional (vereador)	—	**0,01**	0,25	**0,44**

Leitura: Em 2016, nenhum dos três eixos mostra o padrão contemporâneo. PSDB ainda é o partido principal de Pinheiros (36%). O financiamento está na era de transição pós-PJ com PF alta (68%). O ambiente institucional ainda não correlaciona com voto (R^2 = 0,01). **A transformação acontece entre 2016 e 2020**: o PSOL ultrapassa o PSDB em Pinheiros, o FEFC começa a substituir a PF, e o índice institucional passa a ter poder explicativo (R^2 = 0,25). Em 2024, o padrão está consolidado.

Hipótese causal: a polarização nacional 2016–2022 (impeachment-Bolsonaro-Lula) foi um choque político que reorganizou simultaneamente três dimensões do campo político-territorial paulistano: a identidade partidária (PSDB → novas legendas), a estrutura material (PJ → PF → FEFC), e a ativação cultural do ambiente institucional (latente → saliente). Os três processos não são independentes — são manifestações paralelas do mesmo rearranjo.

5.2 Síntese em relação às hipóteses do projeto original

Hipótese	Achado	Status
H1: há novo padrão não-pendular	Confirmada. Pinheiros e Indianópolis começam em PSDB 48% em 2012 e terminam em posições opostas em 2024. Não é pêndulo — é divergência estrutural.	**Confirmada**
H2: maior pluralização implica nova competição	Parcial. NEP caiu (menos partidos efetivos), mas a composição mudou qualitativamente. A 'pluralização' é nova sem ser mais fragmentada.	**Parcial**
H3: centro-direita absorvida pela direita	Confirmada estruturalmente. PSDB 33-44% → 0,6-1,7% nas 8 zonas ricas; substituição por MDB+PRTB+NOVO. Paralelamente, mudança de modelo de captação (PJ/PF → FEFC).	**Confirmada**
H4: voto de esquerda nos bairros ricos aponta para outras variáveis que não renda	**Confirmada de forma decisiva.** Renda explica 9% da variância ideológica; índice institucional explica 44% (66% em métrica alternativa). O ambiente institucional cultural-progressista foi politicamente ativado entre 2016 e 2020 — compatível com Inglehart & Norris.	**Confirmada**

5.3 Diálogo com a literatura

Os achados conversam com cinco tradições de pesquisa:

Inglehart & Norris (2016, 2019) — o argumento de que a clivagem cultural (educação/cosmopolitismo vs nacionalismo/tradicionalismo) substitui a clivagem econômica em democracias contemporâneas recebe aqui evidência brasileira. O ponto de inflexão em SP (2016-2020) é comparável ao Brexit e à eleição de Trump como choques ativadores da dimensão cultural.

Power & Rodrigues-Silveira (2019) — o mapeamento ideológico municipal brasileiro. Este trabalho estende o método deles ao nível infra-municipal (zonas eleitorais dentro de uma mesma cidade), confirmando a tese de reorganização não-pendular da direita brasileira ao longo dos anos 2010.

Soares & Terron (2008) — "Dois Lulas" é o precursor clássico de análise espacial do voto presidencial. Este trabalho aplica a tradição desenvolvendo-a em escala metropolitana com granularidade de zona eleitoral.

Marques (2015) e a escola paulistana de sociologia urbana — a tese de que a hierarquia socioeconômica intra-metropolitana é estruturalmente estável recebe validação aqui: posições relativas das zonas ricas mantiveram-se entre 2010 e 2024, mesmo com variações substanciais de regime político nacional.

Speck & Mancuso (2015) — a literatura sobre financiamento empresarial e sua reforma. Este trabalho identifica que o Fundo Especial reocupou o espaço regulatório aberto pela reforma de 2015, sem passar pelo doador individual — um achado que qualifica a narrativa de "democratização" do financiamento com dados temporais de 4 ciclos municipais.

5.4 Limitações

(a) Censo 2010. A variável "renda" usa dados de 2010, 14 anos antes do voto analisado. Mitigações: (1) a hierarquia relativa de renda das zonas ricas de SP é estruturalmente estável (literatura de sociologia urbana); (2) a defasagem atenua correlações — não as infla — tornando o $R^2 = 0{,}088$ um limite superior conservador; (3) o índice institucional usa base CEM/USP 2022 (contemporânea à eleição), não sofre defasagem.

(b) Índice institucional ad-hoc. O índice é construído por matching de palavras-chave nos nomes dos locais de votação. Refinamentos futuros: (1) cruzar com cadastro Inep (escolas) e cadastros culturais oficiais; (2) validação externa por survey de especialistas em educação paulistana; (3) análise textual do projeto pedagógico das escolas. A robustez do resultado ($R^2 = 0{,}44$) sugere que o índice captura o fenômeno central mesmo com proxy imprecisa.

(c) Análise observacional. Os dados são correlacionais; causalidade só pode ser inferida indiretamente. O teste temporal (Parte III.6) adiciona dimensão plausivelmente causal — o fato do sinal emergir após um choque político identificável é mais compatível com ativação causal do que com correlação espúria. Mas identificação causal rigorosa exigiria desenhos de diferenças-em-diferenças ou experimentos naturais, que estão fora do escopo deste rascunho.

(d) Recorte específico de SP. Os achados são sobre zonas eleitorais da capital paulistana, 2012–2024. A replicação em outras capitais (Rio de Janeiro, Belo Horizonte, Recife) testaria a

generalidade do mecanismo.

5.5 Agenda de pesquisa

Cinco próximos passos metodológicos para a dissertação:

1. Refinamento do índice institucional via cadastros externos (Inep, Secretaria de Cultura, FAPESP) e validação por especialistas em educação paulistana.

2. Replicação em outras capitais brasileiras (Rio de Janeiro, Belo Horizonte, Porto Alegre, Curitiba, Recife). Se o padrão se repete, é mecanismo geral. Se não se repete, é específico de SP — e exige explicação local.

3. Análise individual de candidato × local (em vez de agregação por zona): para cada local de votação, regressão escore ~ tipo institucional + renda + densidade. ~2.000 observações em vez de 58.

4. Inferência causal rigorosa via diferenças-em-diferenças usando a reforma do financiamento de 2015 como choque exógeno. Pergunta: o aumento do índice institucional como preditor foi acelerado pela reforma?

5. Integração com dados de inscrição USP/Mackenzie/PUC por origem: proporção de eleitores na zona que são alunos ou funcionários dessas instituições — teste de mecanismo direto.

5.6 Reprodutibilidade

Todo o código e os dados processados estão em repositório público: github.com/miaguchi/democracia-em-dados. O repositório contém 19 scripts Python (pipelines de ingestão, processamento e análise), 3 relatórios PDF independentes (base para este documento consolidado), 18 gráficos PNG e 13 CSVs de saída. Todas as dependências são conhecidas (pandas, geopandas, matplotlib, statsmodels, esda/libpysal, reportlab, geobr) e instaláveis via conda-forge. Dados primários baixados via *TSEDownloader* (classe própria com download atômico e validação de Content-Length) do CDN do TSE. Geometrias via pacote *geobr*. Base de locais de votação baixada manualmente do portal DataCEM/USP.

Referências selecionadas

Bartolini, S.; Mair, P. (1990). *Identity, Competition and Electoral Availability: The Stabilization of European Electorates 1885–1985*. Cambridge University Press.

Bolognesi, B.; Ribeiro, E.; Codato, A. (2023). "Uma Nova Classificação Ideológica dos Partidos Políticos Brasileiros". *Dados*, 66(2).

Curi, H. (2022). "Ninho dos Tucanos: o PSDB em São Paulo (1994–2018)". *Opinião Pública*, 27.

Inglehart, R.; Norris, P. (2016). "Trump, Brexit, and the Rise of Populism: Economic Have-Nots and Cultural Backlash". HKS Working Paper RWP16-026.

Inglehart, R.; Norris, P. (2019). *Cultural Backlash: Trump, Brexit, and Authoritarian Populism*. Cambridge University Press.

Limongi, F.; Mesquita, L. (2008). "Estratégia partidária e preferência dos eleitores: as eleições municipais em São Paulo entre 1985 e 2004". *Novos Estudos CEBRAP*, 81.

Marques, E. (2015). *A metrópole de São Paulo no século XXI: espaços, heterogeneidades e desigualdades*. Editora UNESP.

Mancuso, W. P.; Speck, B. W. (2015). "Financiamento empresarial na eleição para deputado federal (2002–2010): determinantes e consequências". *Teoria & Sociedade*, 23(2).

Miaguchi, T. S. C. (2023). "Disputa partidária e comportamento político nos bairros ricos de São Paulo (2012–2022)". Proposta de dissertação, DCP/FFLCH-USP.

Pedersen, M. N. (1979). "The Dynamics of European Party Systems: Changing Patterns of Electoral Volatility". *European Journal of Political Research*, 7(1).

Power, T. J. (2010). *Political right in postauthoritarian Brazil: elites, institutions, and democratization*. Penn State Press.

Power, T. J.; Rodrigues-Silveira, R. (2019). "Mapping Ideological Preferences in Brazilian Elections, 1994-2018: A Municipal-Level Study". *Brazilian Political Science Review*, 13(1).

Rocha, C. (2019). "*Menos Marx, mais Mises*: uma gênese da nova direita brasileira (2006-2018)". Tese de Doutorado, Universidade de São Paulo.

Soares, G. A. D.; Terron, S. (2008). "Dois Lulas: a geografia eleitoral da reeleição". *Opinião Pública*, 14(2).

Speck, B. W.; Balbachevsky, E. (2016). "Identificação partidária e voto. As diferenças entre petistas e peessedebistas". *Opinião Pública*, 22(3).

Torres, H. G.; Marques, E.; Ferreira, M. P.; Bichir, R. (2003). "Pobreza e espaço: padrões de segregação em São Paulo". *Estudos Avançados*, 17(47).